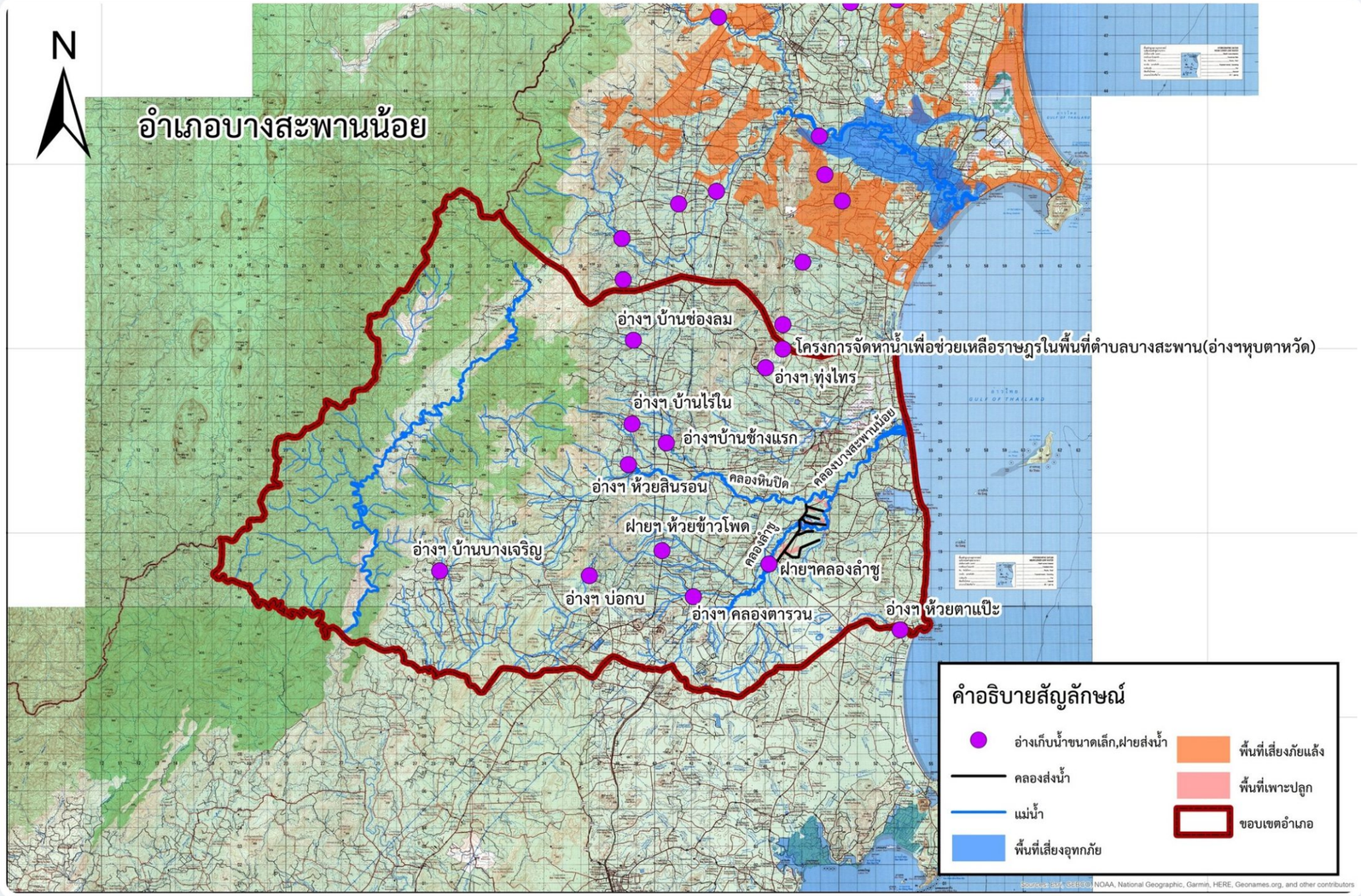
แหล่งน้ำ อำเภอบางสะพานน้อย

ข้อมูล ณ 2 พ.ย. 2569



รวม	อ่างฯ ขนาดให...	อ่างฯ ขนาดเล็ก	ฝาย	อื่นๆ
20 แห่ง	0 แห่ง	14 แห่ง	2 แห่ง	4 แห่ง

อ่างเก็บน้ำขนาดเล็ก 14 แห่ง

ความจุรวม 5.120 ล้าน ลบ.ม. · มีรายงานน้ำ 2 แห่ง 0.538/0.538 (100%) · เต็มอ่าง 2

สรุปแหล่งน้ำรายตำบล

แห่ง · ความจุ ล้าน ลบ.ม.

ตำบล	กลาง/ใหญ่	เล็ก	ฝาย	อื่นๆ	รวม	ความจุ
ช้างแรก	–	5	–	2	**7**	**3.466**
บางสะพาน	–	2	–	–	**2**	**0.153**
ปากแพรก	–	–	–	–	**0**	**–**
ไชยราช	–	1	–	–	**1**	**0.332**
ทรายทอง	–	2	2	1	**5**	**0.672**
รวมทั้งอำเภอ (นอกเขต/ไม่ระบุ 5)					**20**	**5.120**

ภาพรวมอำเภอบางสะพานน้อย

พื้นที่ 692 ตร.กม. · 5 ตำบล · ทางน้ำรวมประมาณ 1,139 กม. (มีน้ำตลอดปี 297 กม.)

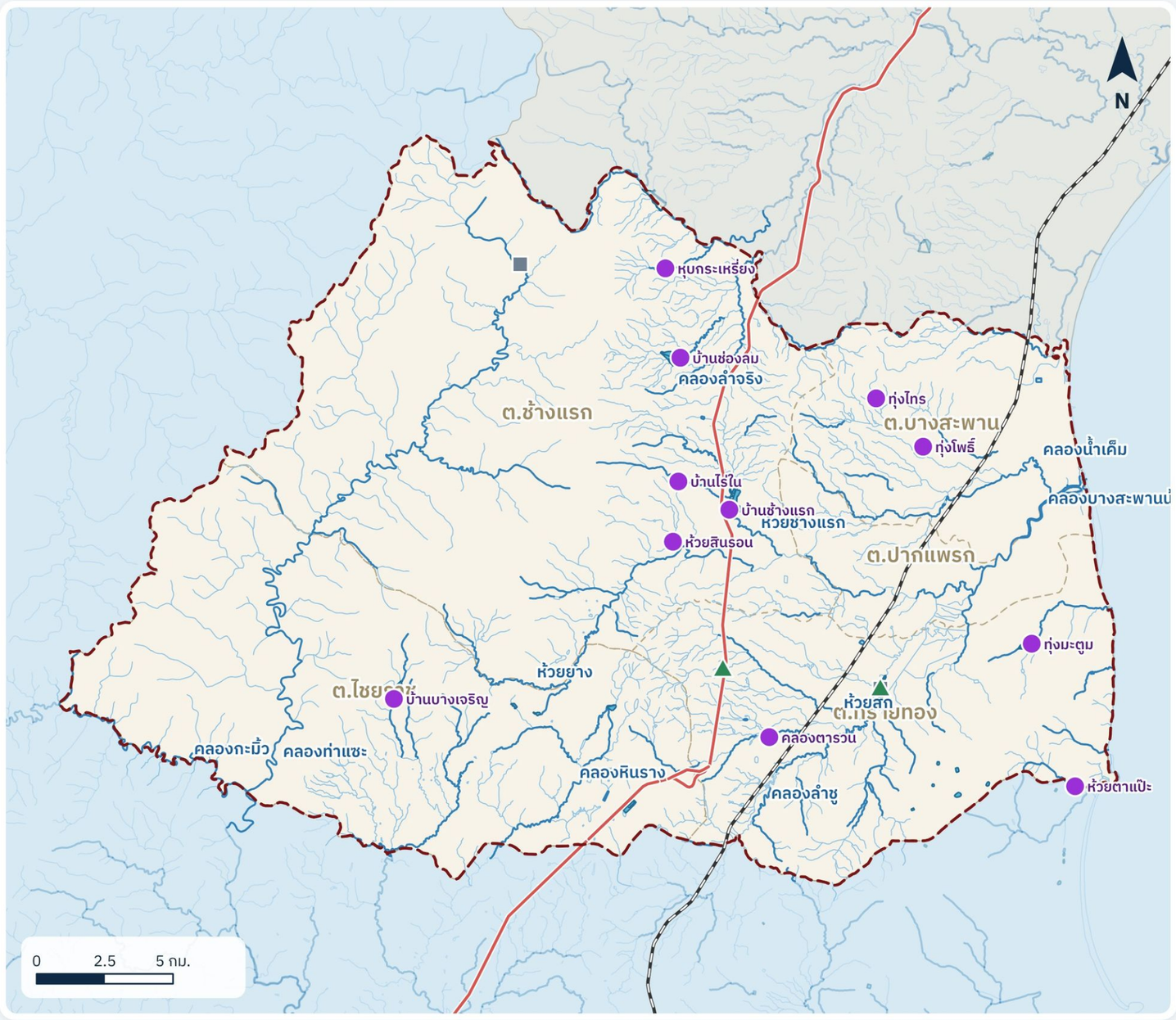
ทางน้ำสายสำคัญ: คลองท่าแซะ · ห้วยยาง · คลองน้ำเค็ม · คลองลำชู · คลองบางสะพานน้อย

ที่มา: แผนที่พื้นที่เสี่ยงอุทกภัย–ภัยแล้ง อำเภอบางสะพานน้อย · ทะเบียนโครงการ คป.ประจวบคีรีขันธ์ · ปริมาณน้ำอ่างฯ ขนาดกลาง 2 พ.ย. 2569 และอ่างฯ ขนาดเล็กประจำสัปดาห์ 30 ต.ค. 2569 · สชป.14

กรมชลประทาน · โครงการชลประทานประจวบคีรีขันธ์

แผนที่ทางน้ำ อำเภอบางสะพานน้อย

สำนักงานชลประทานที่ 14



พื้นที่อำเภอ	ทางน้ำรวม	มีน้ำตลอดปี	แหล่งน้ำ
692 ตร.กม.	1,139 กม.	297 กม.	20 แห่ง

ทางน้ำสายสำคัญ

ความยาวในเขตอำเภอ (กม.) โดยประมาณ

1. คลองท่าแซะ	46.4
2. ห้วยยาง	22.1
3. คลองน้ำเค็ม	15.9
4. คลองลำชู	13.7
5. คลองบางสะพานน้อย	13.2
6. คลองกะมิ้ว	10.6
7. ห้วยสัก	10.5
8. คลองลำจริง	9.3

ข้อมูลรายตำบล

ตำบล	ตร.กม.	ทางน้ำ กม.	แหล่งน้ำ	ทางน้ำสายหลัก
ช้างแรก	276.6	452	7	คลองท่าแซะ
บางสะพาน	69.1	132	2	คลองน้ำเค็ม
ปากแพรก	35.9	57	0	คลองบางสะพานน้อย
ไชยราช	183.0	268	1	คลองท่าแซะ
ทรายทอง	127.5	230	5	คลองลำชู

สัญลักษณ์

- ทางน้ำสายหลัก
- มีน้ำไหลตลอดปี
- มีน้ำไหลไม่ตลอดปี
- ถนนเพชรเกษม
- ทางรถไฟ
- ขอบเขตอำเภอ
- อ่างฯ ขนาดกลาง/ใหญ่
- อ่างฯ ขนาดเล็ก
- ฝาย
- แหล่งน้ำ/ระบบอื่น

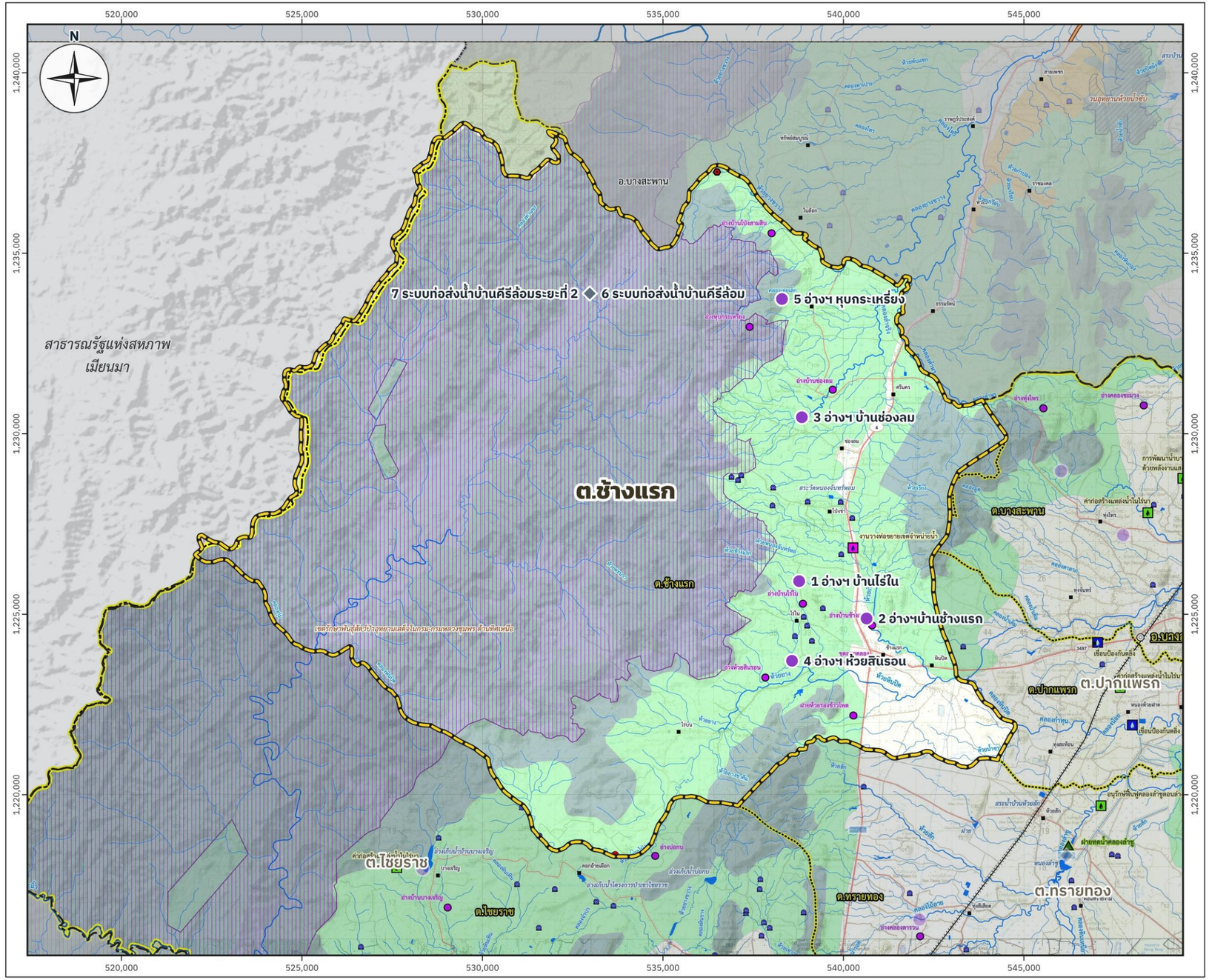
ที่มา: ชั้นข้อมูลทางน้ำ (Stream_rid14) ขอบเขตอำเภอ/ตำบล ถนน ทางรถไฟ สชป.14 · ตำแหน่งแหล่งน้ำจากทะเบียนโครงการ คป.ประจวบคีรีขันธ์ · ความยาวทางน้ำคำนวณโดยประมาณ

แผนที่แสดงทางน้ำและแหล่งน้ำ

มาตราส่วน 1:50,000 (เมื่อพิมพ์ขนาด A1)

0 — 2.5 — 5 กิโลเมตร

ต.ช้างแรก อ.บางสะพานน้อย จ.ประจวบคีรีขันธ์



กรมชลประทาน

โครงการชลประทานประจวบคีรีขันธ์

สำนักงานชลประทานที่ 14

ตำบลช้างแรก · อำเภอบางสะพานน้อย

ตำแหน่งตำบลในอำเภอบางสะพานน้อย



พื้นที่ ตร.กม.	ทางน้ำ กม.	ตลอดปี กม.	แหล่งน้ำ
276.6	452	105.9	7

แหล่งน้ำในต.ช้างแรก

		ความจุ / น้ำ (ล้าน ลบ.ม.)
1	อ่างฯ บ้านไร่ใน	0.114
2	อ่างฯบ้านช้างแรก	1.800
3	อ่างฯ บ้านช่องลม	0.414
4	อ่างฯ ห้วยสินรอน	1.000
5	อ่างฯ หุบกระเหรี่ยง	0.138
6	ระบบท่อส่งน้ำบ้านคีรีล้อม	–
7	ระบบท่อส่งน้ำบ้านคีรีล้อมระยะที่ 2	–

สัญลักษณ์

- แม่น้ำ, คลอง
- แหล่งน้ำ, อ่างเก็บน้ำ
- ถนนสายหลัก
- ทางรถไฟ
- ขอบเขตตำบล
- ขอบเขตอำเภอ
- อ่างเก็บน้ำขนาดใหญ่
- อ่างเก็บน้ำขนาดกลาง
- อ่างเก็บน้ำขนาดเล็ก
- ฝาย/อาคารทดน้ำ
- ระบบส่งน้ำ/อื่น ๆ
- โครงการที่มีต้นเรื่อง
- เขตป่าเพื่อเศรษฐกิจ (E)
- เขตป่าเพื่อการอนุรักษ์ (C)
- เขตรักษาพันธุ์สัตว์ป่า
- พื้นที่กันออก

พื้นหลัง: แผนที่ที่ปรึกษา (ข้อมูลแผนที่ภูมิประเทศ 1:50,000)

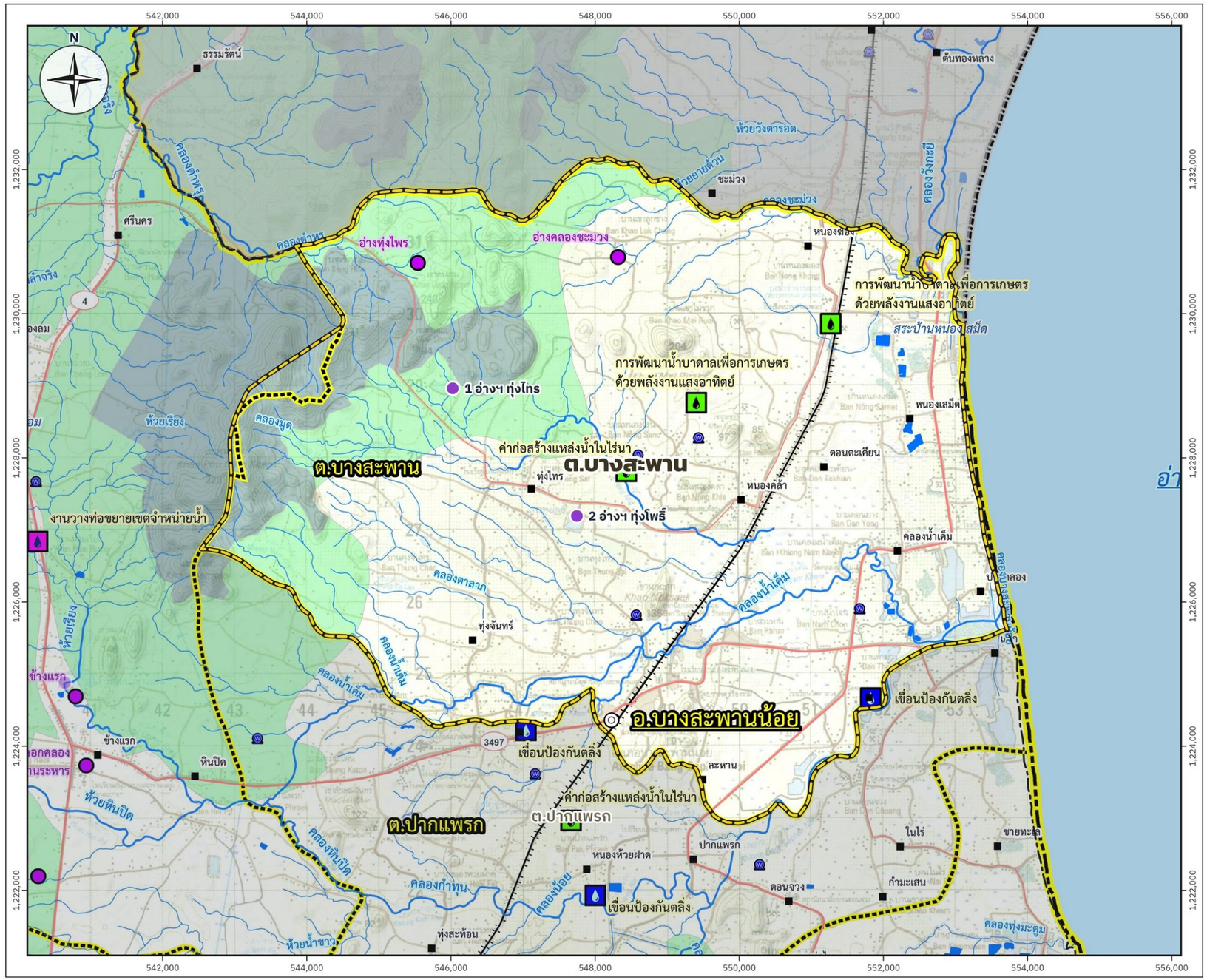
ระบบพิกัด UTM โซน 47N (WGS84)

แผนที่แสดงทางน้ำและแหล่งน้ำ

มาตราส่วน 1:25,000 (เมื่อพิมพ์ขนาด A1)

0 — 1 — 2 กิโลเมตร

ต.บางสะพาน อ.บางสะพานน้อย จ.ประจวบคีรีขันธ์



กรมชลประทาน

โครงการชลประทานประจวบคีรีขันธ์

สำนักงานชลประทานที่ 14

ตำบลบางสะพาน · อำเภอบางสะพานน้อย

ตำแหน่งตำบลในอำเภอบางสะพานน้อย



พื้นที่ ตร.กม.	ทางน้ำ กม.	ตลอดปี กม.	แหล่งน้ำ
69.1	132	35.9	2

แหล่งน้ำในต.บางสะพาน

		ความจุ / น้ำ (ล้าน ลบ.ม.)
1	อ่างฯ ทุ่งไทร	0.153
2	อ่างฯ ทุ่งโพธิ์	–

สัญลักษณ์

- แม่น้ำ, คลอง
- แหล่งน้ำ, อ่างเก็บน้ำ
- ถนนสายหลัก
- ทางรถไฟ
- ขอบเขตตำบล
- ขอบเขตอำเภอ
- อ่างเก็บน้ำขนาดใหญ่
- อ่างเก็บน้ำขนาดกลาง
- อ่างเก็บน้ำขนาดเล็ก
- ฝาย/อาคารทดน้ำ
- ระบบส่งน้ำ/อื่น ๆ
- โครงการที่มีต้นเรื่อง
- เขตป่าเพื่อเศรษฐกิจ (E)
- เขตป่าเพื่อการอนุรักษ์ (C)
- เขตรักษาพันธุ์สัตว์ป่า
- พื้นที่กันออก

พื้นหลัง: แผนที่ที่ปรึกษา (ซ้อนแผนที่ภูมิประเทศ 1:50,000)

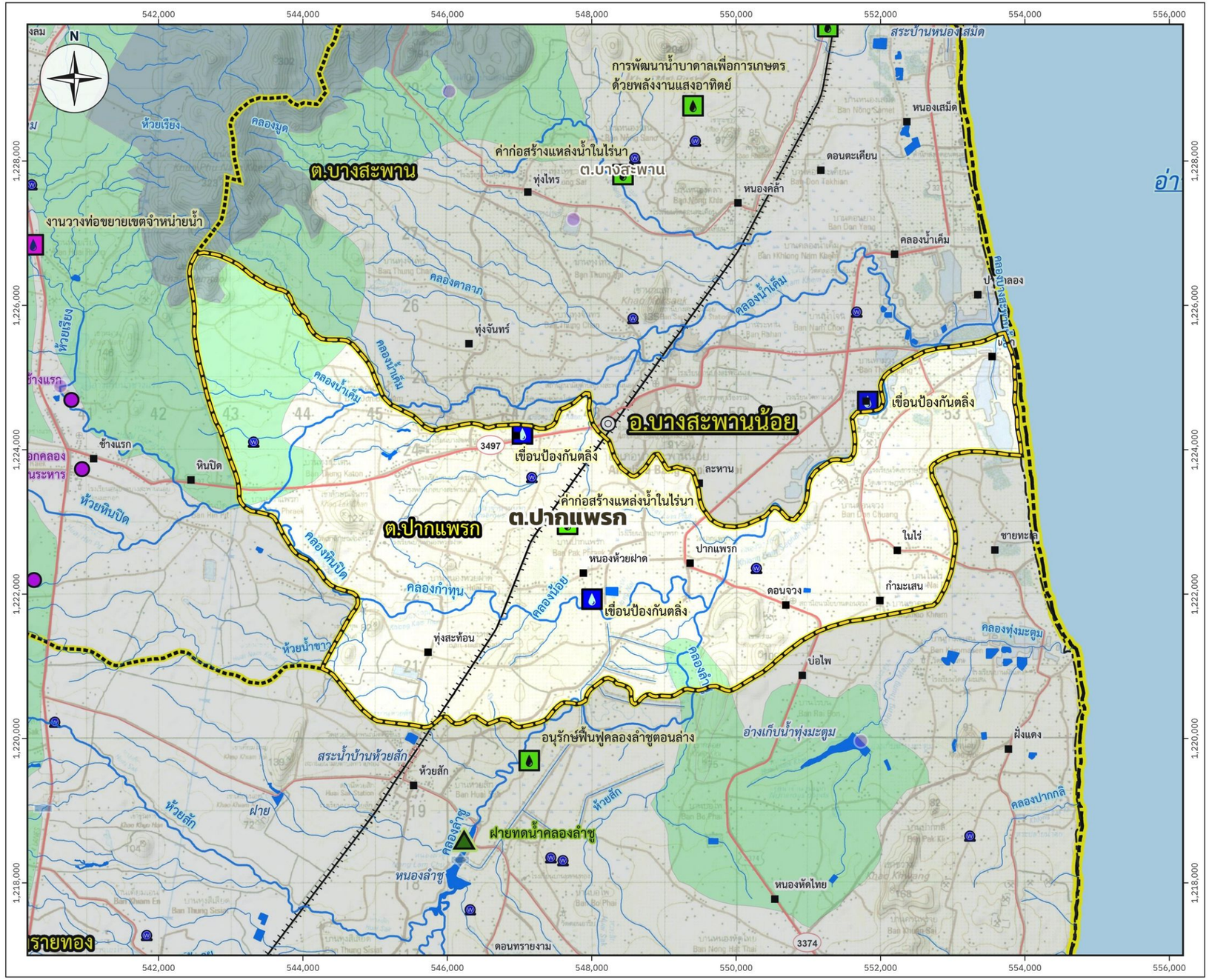
ระบบพิกัด UTM โซน 47N (WGS84)

แผนที่แสดงทางน้ำและแหล่งน้ำ

มาตราส่วน 1:25,000 (เมื่อพิมพ์ขนาด A1)

0 1 2 กิโลเมตร

ต.ปากแพรก อ.บางสะพานน้อย จ.ประจวบคีรีขันธ์



กรมชลประทาน

โครงการชลประทานประจวบคีรีขันธ์

สำนักงานชลประทานที่ 14

ตำบลปากแพรก · อำเภอบางสะพานน้อย

ตำแหน่งตำบลในอำเภอบางสะพานน้อย



พื้นที่ ตร.กม.	ทางน้ำ กม.	ตลอดปี กม.	แหล่งน้ำ
35.9	57	18.5	0

แหล่งน้ำในต.ปากแพรก ความจุ / น้ำ (ล้าน ลบ.ม.)

ไม่พบแหล่งน้ำในทะเบียนโครงการ

สัญลักษณ์

- แม่น้ำ, คลอง
- แหล่งน้ำ, อ่างเก็บน้ำ
- ถนนสายหลัก
- ทางรถไฟ
- ขอบเขตตำบล
- ขอบเขตอำเภอ
- อ่างเก็บน้ำขนาดใหญ่
- อ่างเก็บน้ำขนาดกลาง
- อ่างเก็บน้ำขนาดเล็ก
- ฝาย/อาคารทดน้ำ
- ระบบส่งน้ำ/อื่น ๆ
- โครงการที่มีต้นเรื่อง
- เขตป่าเพื่อเศรษฐกิจ (E)
- เขตป่าเพื่อการอนุรักษ์ (C)
- เขตรักษาพันธุ์สัตว์ป่า
- พื้นที่กันออก

พื้นหลัง: แผนที่ที่ปรึกษา (ซ้อนแผนที่ภูมิประเทศ 1:50,000)

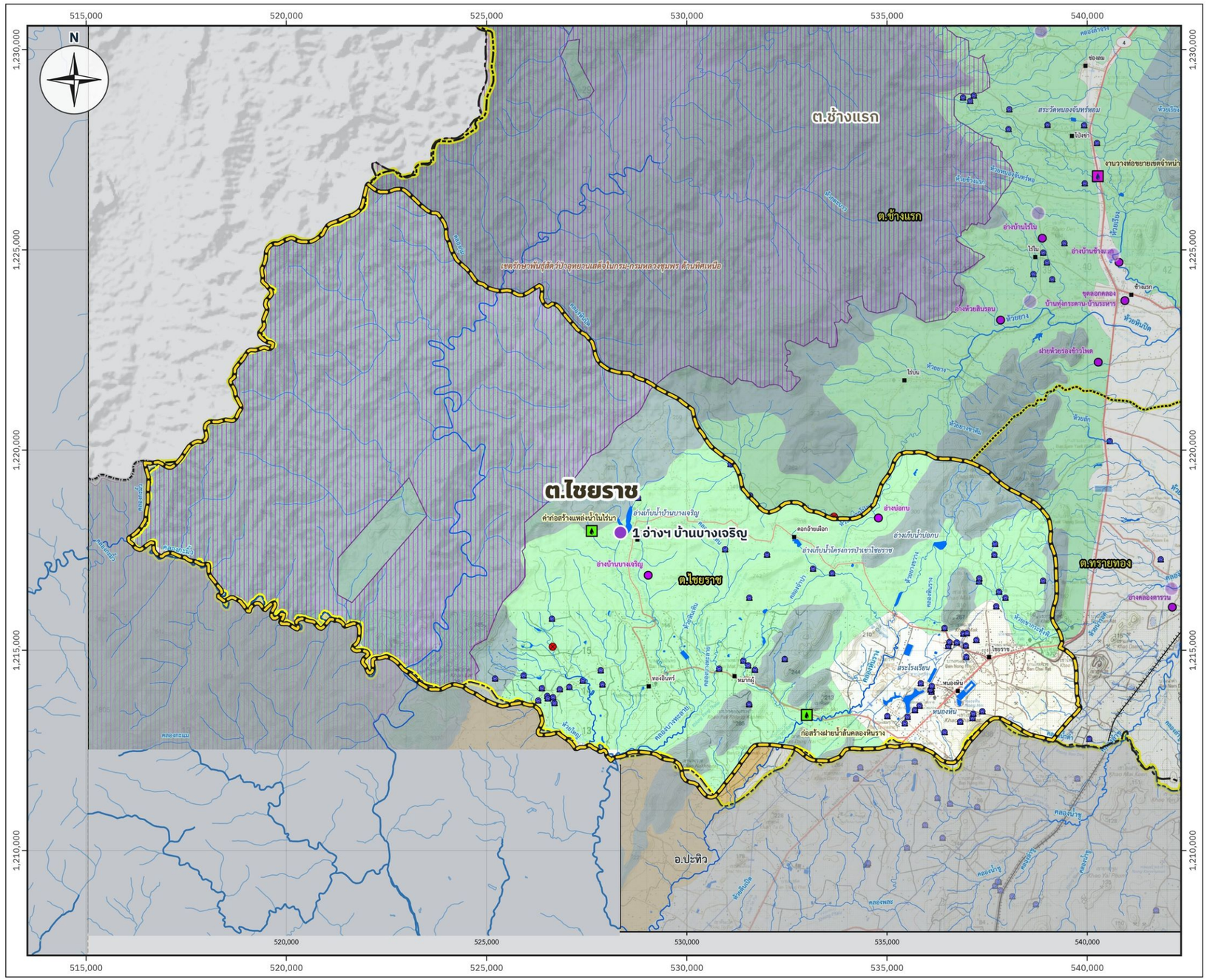
ระบบพิกัด UTM โซน 47N (WGS84)

แผนที่แสดงทางน้ำและแหล่งน้ำ

มาตราส่วน 1:45,000 (เมื่อพิมพ์ขนาด A1)

0 — 2.5 — 5 กิโลเมตร

ต.ไชยราช อ.บางสะพานน้อย จ.ประจวบคีรีขันธ์



กรมชลประทาน

โครงการชลประทานประจวบคีรีขันธ์

สำนักงานชลประทานที่ 14

ตำบลไชยราช · อำเภอบางสะพานน้อย

ตำแหน่งตำบลในอำเภอบางสะพานน้อย



พื้นที่ ตร.กม.	ทางน้ำ กม.	ตลอดปี กม.	แหล่งน้ำ
183.0	268	78.9	1

แหล่งน้ำในต.ไชยราช

		ความจุ / น้ำ (ล้าน ลบ.ม.)
1	อ่างฯ บ้านบางเจริญ	0.332

สัญลักษณ์

- แม่น้ำ, คลอง
- แหล่งน้ำ, อ่างเก็บน้ำ
- ถนนสายหลัก
- ทางรถไฟ
- ขอบเขตตำบล
- ขอบเขตอำเภอ
- อ่างเก็บน้ำขนาดใหญ่
- อ่างเก็บน้ำขนาดกลาง
- อ่างเก็บน้ำขนาดเล็ก
- ฝาย/อาคารทดน้ำ
- ระบบส่งน้ำ/อื่น ๆ
- โครงการที่มีต้นเรื่อง
- เขตป่าเพื่อเศรษฐกิจ (E)
- เขตป่าเพื่อการอนุรักษ์ (C)
- เขตรักษาพันธุ์สัตว์ป่า
- พื้นที่กันออก

พื้นหลัง: แผนที่ที่ปรึกษา (ข้อมูลแผนที่ภูมิประเทศ 1:50,000)

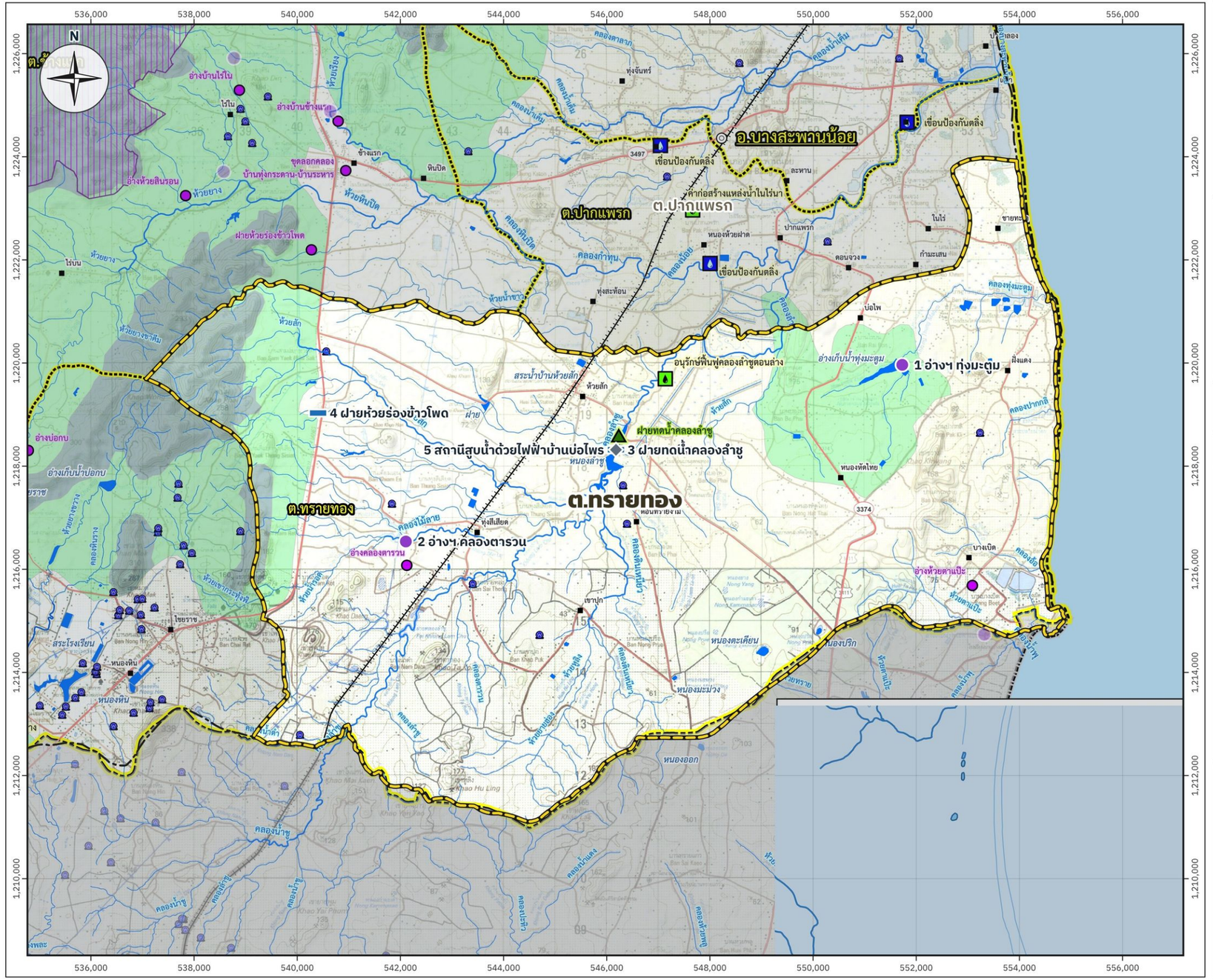
ระบบพิกัด UTM โซน 47N (WGS84)

แผนที่แสดงทางน้ำและแหล่งน้ำ

มาตราส่วน 1:35,000 (เมื่อพิมพ์ขนาด A1)

0 1 2 กิโลเมตร

ต.ทรายทอง อ.บางสะพานน้อย จ.ประจวบคีรีขันธ์


N
536,000
538,000
540,000
542,000
544,000
546,000
548,000
550,000
552,000
554,000
556,000
1,226,000
1,224,000
1,222,000
1,220,000
1,218,000
1,216,000
1,214,000
1,212,000
1,210,000
อ.บางสะพานน้อย
ต.ปากแพรก
ต.ทรายทอง
1 อ่างฯ ทุ่งมะตูม
2 อ่างฯ คลองตารวน
3 ฝายทดน้ำคลองลำชู
4 ฝายห้วยร่องข้าวโพด
5 สถานีสูบน้ำด้วยไฟฟ้าบ้านบ่อไพร
เขื่อนป้องกันตลิ่ง
อนุรักษ์พื้นฟูคลองลำชูตอนล่าง
ฝายทดน้ำคลองลำชู
อ่างเก็บน้ำทุ่งมะตูม
อ่างคลองตารวน
ห้วยลัก
ห้วยยาง
ห้วยหินปิด
คลองลำชู
คลองน้ำใส
คลองน้ำเค็ม
คลองตาลาก
คลองกำทุน
คลองทุ่งมะตูม
คลองปากทศี
คลองสิงหเทพนิมิต
คลองน้ำชู
หนองตะเคียน
หนองมะปาง
หนองออก
หนองบริก
หนองหัดไทย
หนองหิน
ทุ่งสะท้อน
ทุ่งจันทร์
ทุ่งสิเสียด
ช้างแรก
ปากแพรก
บ่อไพ
ไชยราช
ทรายทอง
บางสะพาน
ฝั่งแดง
บางเบิด
ตอนจวง
กำมะเสน
ในไร่
ชายทะเล
ละหาน
ทับคล้อ
ไร่ใน
ไร่นอ
ไร่ใหญ่
ไร่ใต้
ไร่ใหม่
ไร่ใหม่ใต้
ไร่ใหม่เหนือ
ไร่ใหม่ตะวันออก
ไร่ใหม่ตะวันตก
ไร่ใหม่ตะวันตกเฉียงใต้
ไร่ใหม่ตะวันตกเฉียงเหนือ
ไร่ใหม่ตะวันออกเฉียงใต้
ไร่ใหม่ตะวันออกเฉียงเหนือ